פרט פתח לחלון ②
1 : 20

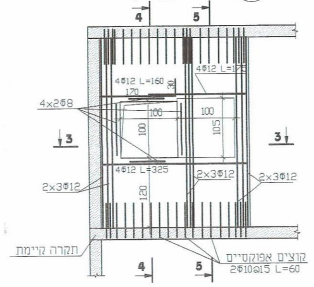

4
5
4Φ12 L=175
4Φ12 L=160
170
30
4x2Φ8
100
100
100
105
3
3
4Φ12 L=325
2x3Φ12
2x3Φ12
2x3Φ12
120
תקרה קיימת
קוצים אפוקסיים
2Φ10@15 L=60
4
5

חתך 3-3
1 : 20

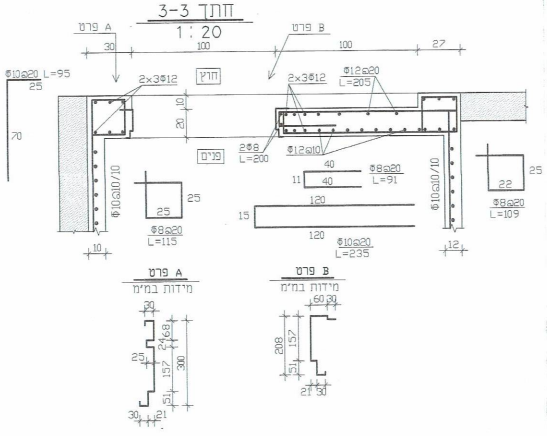

פרט A
פרט B
30
100
100
27
Φ10@20 L=95
25
70
2x3Φ12
חוץ
2x3Φ12
Φ12@20
L=205
10
20
פנים
2Φ8
L=200
Φ12@10
Φ10@10/10
Φ10@10/10
25
25
Φ8@20
L=115
40
11
40
Φ8@20
L=91
120
15
120
Φ10@20
L=235
25
22
Φ8@20
L=109
10
12

פרט A
מידות במ"מ

פרט B
מידות במ"מ

30
24
68
25
157
300
51
30
21
60
30
208
157
51
21
30

חתך 4-4
1 : 20

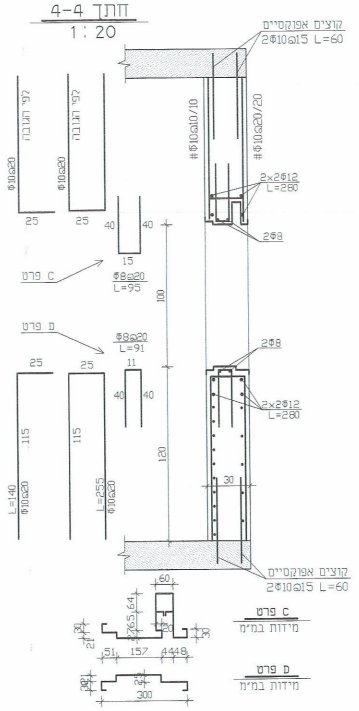

קוצים אפוקסיים
2Φ10@15 L=60
לפי הגובה
לפי הגובה
Φ10@20
Φ10@20
#Φ10@10/10
#Φ10@20/20
2x2Φ12
L=280
25
25
40
40
2Φ8
15
פרט C
Φ8@20
L=95
100
פרט D
Φ8@20
L=91
11
2Φ8
25
25
40
40
2x2Φ12
L=280
115
115
120
30
L=140
Φ10@20
L=255
Φ10@20
קוצים אפוקסיים
2Φ10@15 L=60
60
65
64
27
20
30
30
21
51
157
44
48
30
21
25
300

פרט C
מידות במ"מ

פרט D
מידות במ"מ

חתך 5-5
1 : 20

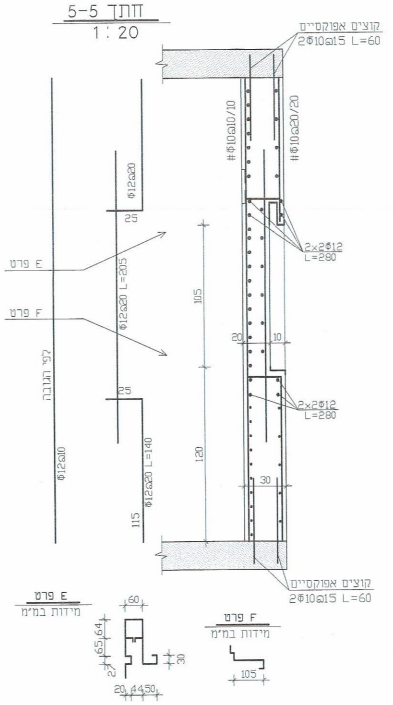

קוצים אפוקסיים
2Φ10@15 L=60
#Φ10@10/10
#Φ10@20/20
Φ12@20
25
פרט E
פרט F
Φ12@20 L=205
105
2x2Φ12
L=280
20
10
לפי הגובה
25
2x2Φ12
L=280
Φ12@10
120
Φ12@20 L=140
115
30
קוצים אפוקסיים
2Φ10@15 L=60
60
65
64
27
30
20
44
50
105

פרט E
מידות במ"מ

פרט F
מידות במ"מ

פרט פינה אופקית ③
1 : 20

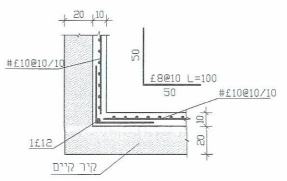

20
10
#£10@10/10
50
£8@10 L=100
50
#£10@10/10
10
20
1£12
קיר קיים

חתך אנכי אופייני דרך קיר חיצוני ④
1 : 20

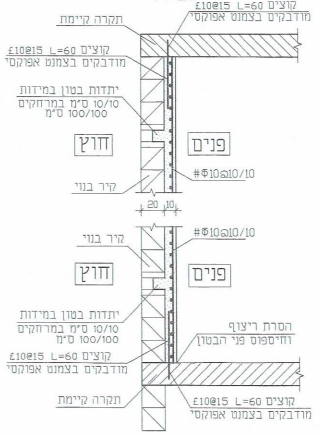

קוצים £10@15 L=60
מודבקים בצמנט אפוקסי
תקרה קיימת
קוצים £10@15 L=60
מודבקים בצמנט אפוקסי
יתדות בטון במידות
10/10 ס"מ במרחקים
100/100 ס"מ
חוץ
פנים
#Φ10@10/10
קיר בנוי
20
10
קיר בנוי
#Φ10@10/10
חוץ
פנים
יתדות בטון במידות
10/10 ס"מ במרחקים
100/100 ס"מ
הסרת ריצוף
וחיספוס פני הבטון
קוצים £10@15 L=60
מודבקים בצמנט אפוקסי
תקרה קיימת
קוצים £10@15 L=60
מודבקים בצמנט אפוקסי

חתך אנכי אופייני דרך קיר פנימי ⑤
1 : 20

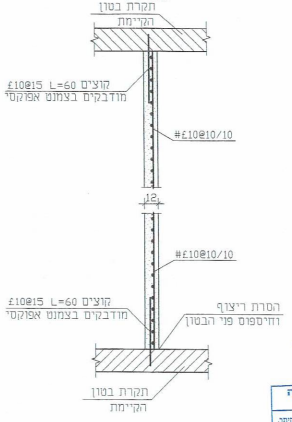

תקרת בטון
הקיימת
קוצים £10@15 L=60
מודבקים בצמנט אפוקסי
#£10@10/10
12
#£10@10/10
קוצים £10@15 L=60
מודבקים בצמנט אפוקסי
הסרת ריצוף
וחיספוס פני הבטון
תקרת בטון
הקיימת

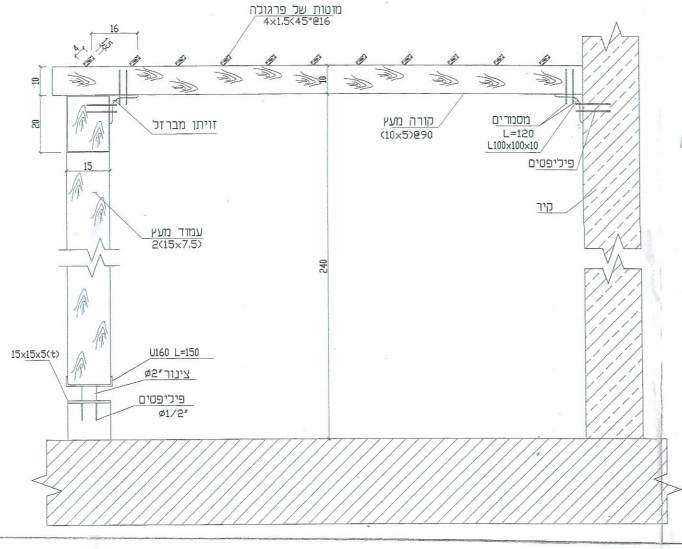

מוטות של פרגולה
4x1.5<45°@16
16
4
1.5
10
20
זויתן מברזל
קורה מעץ
(10x5)@90
מסמרים
L=120
L100x100x10
10
פיליפסים
15
קיר
עמוד מעץ
2(15x7.5)
240
15x15x5(t)
U160 L=150
צינור Φ2"
פיליפסים
Φ1/2"

פרט פרגולה
ק.מ. 1:10

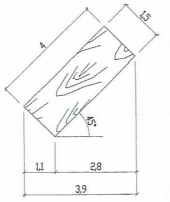

4
1.5
45°
1.1
2.8
3.9

מוטות
ק.מ. 1:1

14.3.13

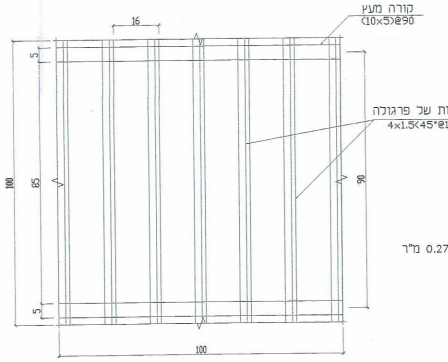

קורה מעץ
(10x5)@90
16
5
מוטות של פרגולה
4x1.5<45°@16
100
85
90
5
100

הרכב הפרגולה

כיסוי לפרגולה לחות עץ
על 1.0 מ"ר דרוש 10 מ.ר. לחות
שטח כיסוי על 1.0 מ"ר–0.0388*7=0.27 מ"ר
שטח קורה–2*0.05*1.00=0.10 מ"ר
יחס כיסוי:
(0.27+0.10)/1.00*100=37%<40%

עיריית תל-אביב-יפו
מינהל ההנדסה / היתרי בניה
...נית מאושרת זו מיום 9.01.13
...הגיש חשבון.
הגיש תוכנית סניטרית 10
אחראי לאזור

הועדה המקומית לתכנון ולבניה
למרחב תכנון תל-אביב - יפו
בהתאם לסעיף 18/ב לתקנות התכנון והבניה (בקשה להיתר, תנאים ואגרות) תש"ל - 1970, הריני לאשר כי לספח זה צורף היתר בניה / שימוש מס' 13-0402
מיום 20.03.13 ומהווה חלק בלתי נפרד ממנו.
תאריך: 20 03 2013 מהנדס העיר

ר 12-1564

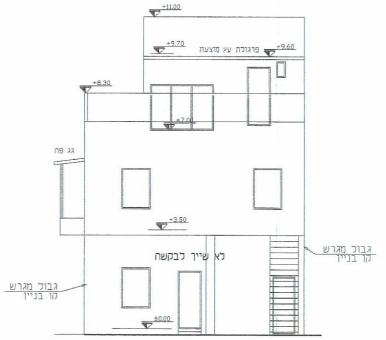
+11.00
+9.70
פרגולת עץ מוצעת
+9.60
+8.30
+7.00
גג פח
+3.50
לא שייך לבקשה
גבול מגרש
קו בניין
גבול מגרש
קו בניין
±0.00

חזית לרח' אביטל ק.מ.1:100

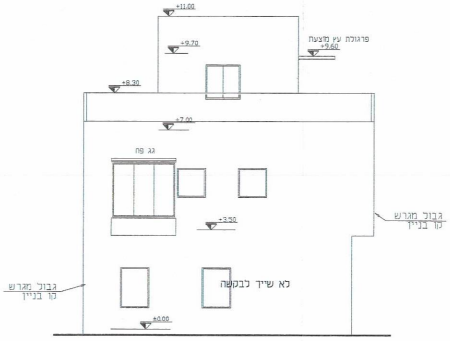
+11.00
+9.70
פרגולת עץ מוצעת
+9.60
+8.30
+7.00
גג פח
+3.50
גבול מגרש
קו בניין
לא שייך לבקשה
גבול מגרש
קו בניין
±0.00

חזית לרח' מושיע ק.מ. 1:100

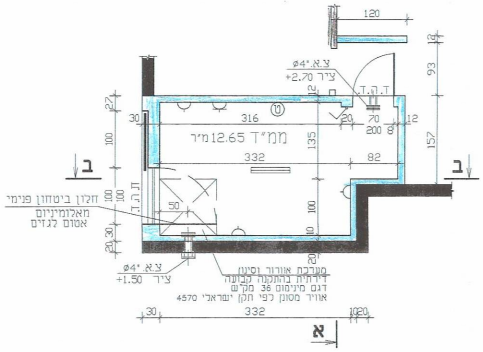
120
ø4" צ.א.
ציר +2.70
ד.ה.ד.
14
93
157
27
30
316
20
70
200
8
12
ממ"ד 12.65 מ"ר
135
332
82
ב
ב
100
100
100
ד.ה.ד.
50
חלון ביטחון פנימי
מאלומיניום
אטום לגזים
30
20
10
20
ø4" צ.א.
ציר +1.50
מערכת אוורור וסינון
דירתית בהתקנה קבועה
דגם מינימום 36 מק"ש
אוויר מסונן כפי תקן ישראלי 4570
30
332
10
20
א

תכנית ממ"ד קומה א'

1 : 50

מקרא

שקע	⌒
טלפון	⌒
טלוויזיה	ⓣ
מפסק	╱
גוף תאורה פלורוסצנטית 36x2 וואט	═

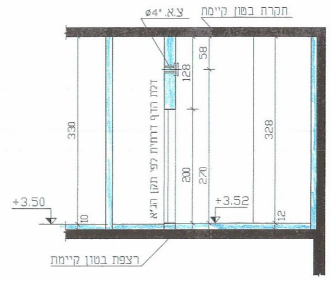
ø4" צ.א.
תקרת בטון קיימת
58
128
330
דלת הדף דחיפה לפי תקנון הג"א
200
270
328
+3.50
10
+3.52
12
רצפת בטון קיימת

חתך א-א

1 : 50

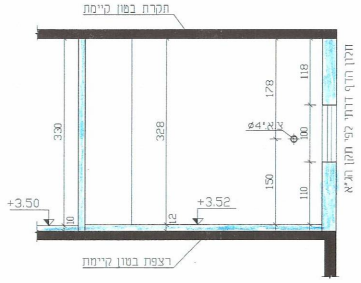
תקרת בטון קיימת
330
328
178
118
ø4" צ.א.
100
150
110
חלון הדף דחיפה לפי תקנון הג"א
+3.50
10
12
+3.52
רצפת בטון קיימת

חתך ב-ב

1 : 50

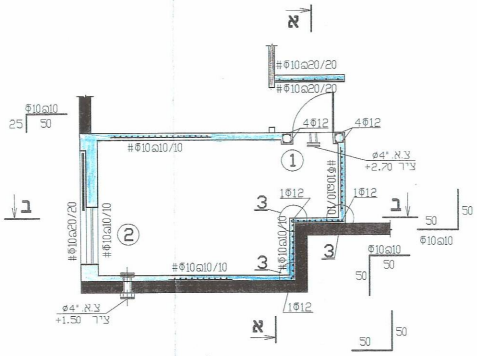
א
#Φ10a20/20
#Φ10a20/20
Φ10a10
25
50
4Φ12
4Φ12
#Φ10a10/10
1
ø4" צ.א.
ציר +2.70
#Φ10a10/10
1Φ12
3
1Φ12
ב
ב
50
50
Φ10a10
#Φ10a20/20
#Φ10a10/10
2
#Φ10a10/10
3
3
Φ10a10
50
50
#Φ10a10/10
ø4" צ.א.
ציר +1.50
1Φ12
א
50
50
Φ10a10

תכנית ממ"ד קומה א'

1 : 50

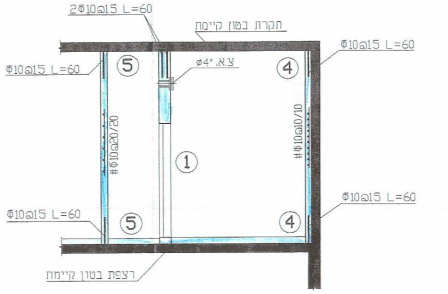
2Φ10a15 L=60
תקרת בטון קיימת
Φ10a15 L=60
5
ø4" צ.א.
4
Φ10a15 L=60
#Φ10a20/20
1
#Φ10a20/20
Φ10a15 L=60
5
4
Φ10a15 L=60
רצפת בטון קיימת

חתך א-א

1 : 50

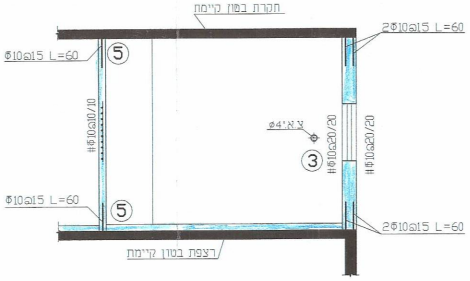
תקרת בטון קיימת
2Φ10a15 L=60
Φ10a15 L=60
5
#Φ10a10/10
ø4" צ.א.
3
#Φ10a20/20
#Φ10a20/20
Φ10a15 L=60
5
2Φ10a15 L=60
רצפת בטון קיימת

חתך ב-ב

1 : 50

פרט פתח לדלת ①

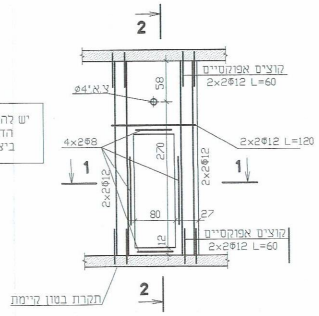
2
קוצים אפוקסיים
2x2Φ12 L=60
ø4" צ.א.
58
4x2Φ8
2x2Φ12 L=120
270
1
1
2x2Φ12
2x2Φ12
80
27
12
קוצים אפוקסיים
2x2Φ12 L=60
תקרת בטון קיימת
2

יש להרכיב את משקוף
הדלת במקומו לפני
ביצוע יציקת במון

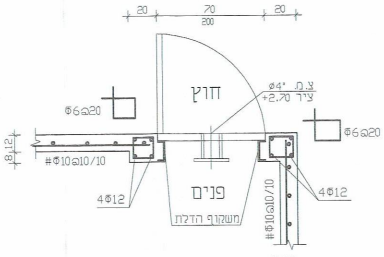
20
70
20
200
חוץ
ø4" צ.מ.
ציר +2.70
Φ6a20
Φ6a20
8
12
#Φ10a10/10
4Φ12
פנים
4Φ12
משקוף הדלת
#Φ10a10/10
8
12

חתך 1-1

1 : 20

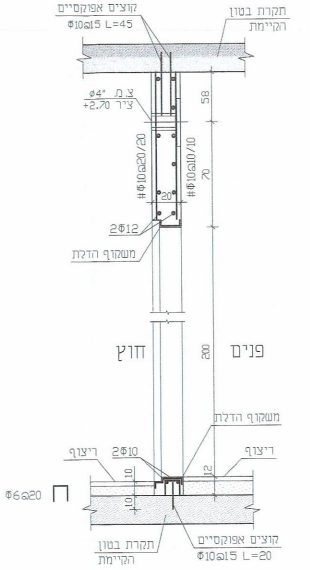
קוצים אפוקסיים
Φ10a15 L=45
תקרת בטון
הקיימת
ø4" צ.מ.
ציר +2.70
58
#Φ10a20/20
#Φ10a10/10
70
20
2Φ12
משקוף הדלת
חוץ
200
פנים
משקוף הדלת
ריצוף
2Φ10
ריצוף
10
12
Φ6a20
10
תקרת בטון
הקיימת
קוצים אפוקסיים
Φ10a15 L=20

חתך 2-2

1 : 20

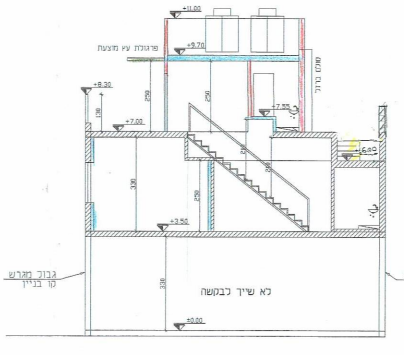
+11.00
+9.70
פרגולה עץ מוצעת
+8.30
+7.00
+7.55
+6.40
+3.50
±0.00
גבול מגרש
קו בניין
לא שייך לבקשה

חתך א-א ק.מ. 1:100

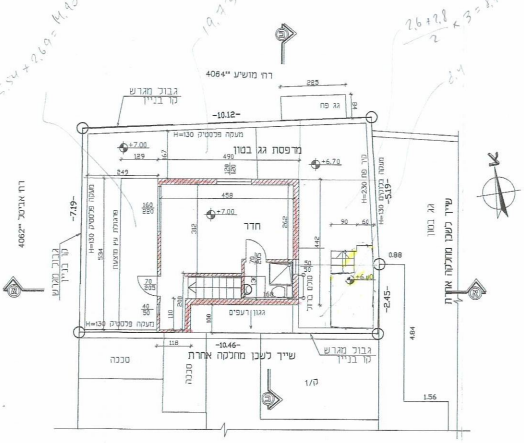
רח' מושיע 4064
רח' אביטל 4062
גבול מגרש
קו בניין
גג פח
-10.12-
-7.19-
-5.19-
-2.45-
-10.46-
מעקה פלסטיק H=130
מרפסת גג בטון
+7.00
+6.70
חדר
+7.00
גגון רעפים
שייך לשכן מחזקה אחרת
סככה
0.88
4.84
1.56

סה"כ מרפסות
14.9 + 19.23 + 8.1 + 8.4 = 51

5.54 + 2.69 = 14.90

19.23

$\frac{2.6+2.8}{2} \times 3 = 8.1$

8.4

תכנית קומת גג ק.מ. 1:100

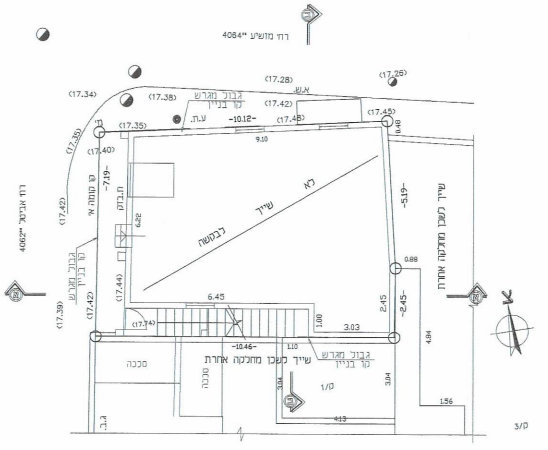
רח' מושיע 4064
רח' אביטל 4062
גבול מגרש
קו בניין
(17.28)
(17.26)
(17.34)
(17.38)
(17.42)
(17.48)
(17.45)
(17.35)
(17.40)
-10.12-
-7.19-
-5.19-
-2.45-
-10.46-
לא שייך לבקשה
6.45
3.03
שייך לשכן מחזקה אחרת
סככה
0.88
4.84
1.56
4.13
3/ס

תכנית קרקע ק.מ. 1:100

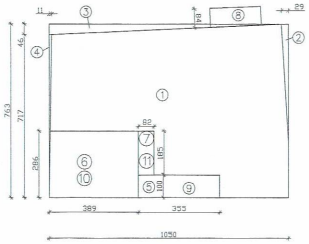
①
②
③
④
⑤
⑥
⑦
⑧
⑨
⑩
⑪
225
29
11
763
717
46
286
82
185
389
355
1050

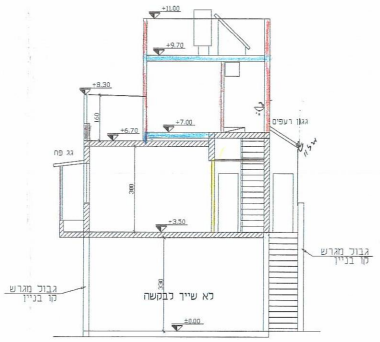
+11.00
+9.70
+8.30
+7.00
+6.70
+3.50
±0.00
גגון רעפים
גג פח
גבול מגרש
קו בניין
לא שייך לבקשה

חתך ב-ב ק.מ. 1:100

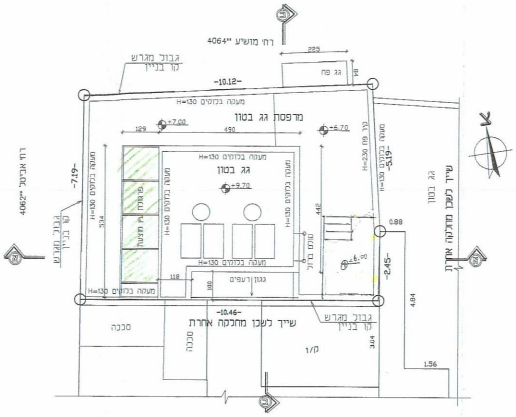
רח' מושיע 4064
רח' אביטל 4062
גבול מגרש
קו בניין
-10.12-
-7.19-
-5.19-
-2.45-
-10.46-
מעקה בלוקים H=130
מרפסת גג בטון
+7.00
+6.70
גג בטון
+9.70
גגון רעפים
שייך לשכן מחזקה אחרת
סככה
0.88
4.84
1.56

תכנית קומת גג עליון ק.מ. 1:100

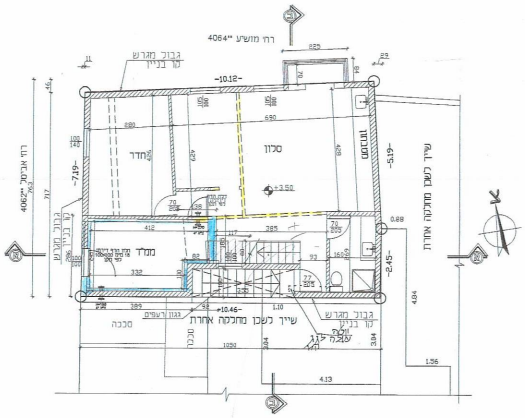
רח' מושיע 4064
רח' אביטל 4062
גבול מגרש
קו בניין
-10.12-
-7.19-
-5.19-
-2.45-
-10.46-
חדר
סלון
ממ"ד
+3.50
גגון רעפים
שייך לשכן מחזקה אחרת
סככה
0.88
4.84
1.56
4.13

תכנית קומה א' ק.מ. 1:100

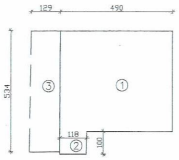
129
490
534
442
①
②
③
118
100

סה"כ מרפסות
68,73
− 22,84
45,89

חישוב שטחים

קומה א'

שטח דירה קיים

מסגרת
①7.63x10.50=80.11 ✓

הורדות
②0.29x7.63=2.21 ✓
③0.46x10.50=4.83 ✓
④0.11x7.17=0.79 ✓
⑤1.00x3.55=3.55 ✓
⑥2.86x3.89=11.13 ✓
⑦0.82x1.85=1.52 ✓

24.03

שטח דירה
80.11-24.03=56.08 ✓

56.08
+12.65
68.73

מרפסת מקורה
⑧2.25x0.84=1.89 ✓

גגון כניסה
⑨1.00x3.55=3.55 ✓

ממ"ד
⑩2.86x3.89=11.13 ✓
⑪0.82x1.85=1.52 ✓

ס"כ שטח ממ"ד
11.13+1.52=12.65 ✓

ס"כ שטח דירה
56.08+1.89+3.55+12.65=74.17 ✓
61.52

קומת גג

חדר על הגג
①4.90x4.42=21.66 ✓
②1.18x1.00=1.18 ✓

22.84 ✓
− 1.52
21.32

פרגולה
③1.29x5.34=6.89 ✓

ס"כ שטח דירה לאחר תוספת
74.17+22.84=97.01

✓

מפה טופוגרפית

קנה מידה 1:250

מחוז : תל-אביב
נפה : תל-אביב-יפו
גוש : 6135
חלקה : 44 (חלק)
כתובת : רח, אביטל 28

מטרת המדידה: הגדרת מגרש משני עפ"י תב"ע 2215

שם הבעלים כרשום בנסח טאבו+מס' ת.ז :		
	דוידוב ויטלי	310123278
	דוידוב תמרה	306519794
	יעקוב אילנה	22041917

__שטח לפי נסח :__

שטח החלקה כולה : 11.476 ד.מ.

בעלות בחלקים(כרשום בנסח טאבו) :

דוידוב ויטלי	15/5738
דוידוב תמרה	15/5738
יעקוב אילנה	108/11447

בעלות במיר : 168
שטח מדוד(מיר) : 78
שטח מגרש משני : ד.מ.
שטח לגריעה : ד.מ.

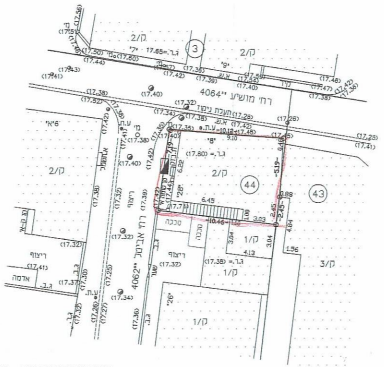

רח' מושיע "4064"
רח' אביטל "4062"
תעלת ניקוז
44
43
3
ק/2
ק/1
ק/3
"8"
"28"
"26"
"9"
"9א"
ריצוף
סככה
אדמה

המפה עודכנה בתאריך : 5.01.2012

א. שמעון

לא לצרכי רישום

תרשים הסביבה 1 : 1250

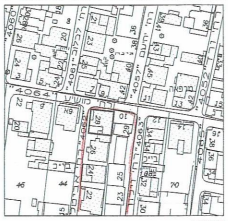

4064
4062
4063
4061
4057
4052
4060
מרפאה

הערות :
1. המספרים בסוגריים מציינים גבהים.
2. הגבהים מבוססים על נ.ג. עירונית מס' 188 שגובהה 17.530 מ'.

הנני מצהיר כי התוכנית ערוכה לפי חוק התכנון והבניה ולפי הנחיות עיריית ת"א-יפו

תל-אביב
תאריך : 7.06.2007

א. שמעון
א.שמעון, מודד מוסמך, רשיון מס' "256"
א.שמעון, רח' רימלט, 12 רמת גן, טל. 052-647718, 03-6741012

130 550 | 130 575 | 130 600 | 162 075 | 162 050

יב. מינויים מטעם מבקש ההיתר - ניתן למנות אדם אחד ליותר מתפקיד אחד. ימולאו פרטיו ליד כל אחד מהתפקידים שהוא ממלא על פי הוראות כל דין.

מינוי עורך הבקשה הראשי ☐
אני ממנה בזה את אליאס הרצל בעל/ת מס זהות 053431235 הרשום בסעיף א להיות עורך הבקשה הראשי להיתר, ולייצגני לפני מוסדות התכנון והרשויות המוסמכות בכל הנוגע לטיפול בבקשה להיתר ולקבלתו, לרבות התיקונים ככל שידרשו הרשויות המוסמכות.

מינוי עורכי בקשה לפי תחומים ☐
אני ממנה בזה את הרשומים להלן להיות עורכי הבקשה להיתר בתחום הפעולה הרשום ליד שמם ולייצגני בתחום פעולתם לפי מוסדות התכנון והרשויות המוסמכות בכל הנוגע לטיפול בבקשה להיתר ולקבלתו לרבות התיקונים ככל שידרשו הרשויות המוסמכות.

שם משפחה ושם פרטי	תחום פעולה	המען	מספר טלפון	מספר פקס
1.	מתכנן האינסטלציה הסניטרית			
2.				

מינוי מתכנן שלד הבניין ☐
אני ממנה בזה את ________ בעל/ת מס זהות ________ הרשום בסע' א להיות אחראי לתיכנון שלד הבניין שבעבורו מבוקש ההיתר, להגיש לוועדה המקומית לרשות הרישוי המקומית את החישובים לגבי הבנייה שבעבורה מבוקש היתר ולפקח פיקוח עליון על הקמת השלד.

מינוי הקבלן האחראי לבניית ☐
☐ אני ממנה בזה את ________ בעל/ת מס זהות ________ ובעל תעודת רישום בפנקס הקבלנים מספר ________ בסדור ________ ובעל רישיון לביצוע עבודה בתוקף עד ________ לבצע את העבודה הנדונה בהיתר כמחוייב לפי כל דין.
☐ אני מצהיר, כי טרם מסרתי את ביצוע העבודה הנדונה בהיתר לידי קבלן, ומתחייב כי אמסור אותה לידי קבלן רשום בפנקס הקבלנים, כמתחייב על פי כל דין, ולהודיע על כך לרשות הרישוי המקומית טרם התחלת ביצוע העבודות, וחתימתו של הקבלן תצורף להודעה המפרטת את פרטי רישומו של הקבלן.

מינוי האחראי לבניית שלד הבניין ☐
☐ אני ממנה בזה את ________ בעל/ת מס זהות ________ כתובת ________ טלפון ________ פקס ________ הרשום לעיל להיות אחראי לביצוע שלד הבניין.
☐ אני מצהיר, כי טרם מיניתי אחראי/ת לביצוע עבודות הבנייה בתחומים האלה: ________ ומתחייב לעשות זאת כמפורט בתקנות, ולהודיע על כך לרשות הרישוי המקומית טרם התחלת ביצוע העבודה.

מינוי אחראים לביקורת ☐
☐ אני ממנה בזה את הרשומים להלן להיות אחראים לביקורת על ביצוע עבודות בתחום הפעולה כרשום ליד שמם

שם משפחה ושם פרטי	תחום פעולה	המען	מספר טלפון	מספר פקס
1.	אחראי ראשי			
2.				
3.				

☐ אני מצהיר כי טרם מיניתי אחראי/ם לביקורת על ביצוע עבודות הבנייה את כולם או את קצתם בתחומים האלה ________ ומתחייב לעשות זאת כמפורט בתקנות, ולהודיע על כך לרשות הרישוי המקומית טרם התחלת ביצוע העבודה.

חתימת המבקש על המינויים X________

יג. הצהרות

הצהרת עורכי הבקשה כולל הצהרת עורך הבקשה על לחץ המים ☐
אנו החתומים מטה מצהירים בזה:
1) כל אחד מאתנו מאשר שהאמור בנוגע לרשימה שבסעיף י"ב לעיל הוא נכון.
2) כל אחד מאתנו מסכים לקבל עליו את התפקיד המיועד לו בסעיף י"ב לעיל.
3) אנו מצהירים, כל אחד בנוגע לתחום פעולתו, שיש לנו כישורים מקצועיים לערוך בקשה זו וכי בדקנו את המסמכים הנוגעים לבקשה, לרבות כל תכנית הנוגעת לבקשה, וידוע לנו כי אם הצהרה זו אינה נכונה, הרי היא תיחשב מסירת ידיעה שהיא כוזבת או מטעה בפרט חשוב, כמשמעותה בסעיף 214 לחוק, וצפויים לנו העונשים הקבועים לפי כל דין.

אני ולנטינה סמולבוב (עורך בקשה ראשי) אחראי/ת לכך שהתבקשת, ובכלל זה נספחות, נערכה לפי מיטב הידיעה המקצועית ובהתאם לכל חיקוק החל על הבניין או העבודה המוצעת, שכל הנתונים שנמסרו על ידי בבקשה זו נכונים ושהתכנון המוצע תואם את כל התכניות, פרט לסטיות שפורטו לעיל.

☐ אני עורך הבקשה מתכנן האינסטלציה הסניטרית, מצהיר בזאת ואחראי לכך שתכניות הבקשה בכל הנוגע לסידורים הסניטריים נערכו כדין וכי קויימו בהן הוראות החוק וההוראות למתקני תברואה התשל"ס 1970 (הל"ת) לענין זה, לרבות בדיקת לחץ המים הקיים בבנין ותיכנון בהתאם.

	תאריך	שם משפחה ושם פרטי	מספר רישיון	חתימה
עורך בקשה ראשי	14.3.13	אליאס הרצל	167781	
עורך בקשה 1 מתכ. הארנס. הסניט.			~~310123278~~	
עורך בקשה 2				

הצהרת מתכנן שלד הבניין ☐
אני החתום מטה (שם משפחה ושם פרטי) אליאס הרצל מס זהות 053431235
מהנדס רשוי מס ________/הנדסאי בעל רישיון מס 167781 (ל"מבנה פשוט") מצהיר בזאת כדלקמן:
1) אני מסכים להיות מתכנן שלד הבניין הנדון בבקשה ולפקח פיקוח עליון על הקמת השלד.
2) אני מתחייב להגיש לפני מתן ההיתר, נושא הבקשה את החישובים הסטטיים בדבר הבנייה שבעבורה ההיתר.
3) ידוע לי, שאם אחרי הגשת הנתונים הסטטיים יתגלה צורך בשינוי מהותי בהם, אני מתחייב להגיש חישובים סטטיים מתוקנים מיד עם גילוי הצורך בכך.
4) אני מצהיר, כי יש לי כישורים מקצועיים לערוך בקשה זו וכי בדקתי את כל המסמכים הנוגעים לבקשה, לרבות כל תכנית הנוגעת לבקשה, וידוע לי כי אם הצהרה זו אינה נכונה, הרי היא תיחשב מסירת ידיעה שהיא כוזבת או מטעה בפרט חשוב, כמשמעותה בסעיף 214 לחוק, וצפויים לי העונשים הקבועים לפי כל דין.
5) ידוע לי כי עלי לשמור את תכניות הקונסטרוקציה לתקופה של לא פחות מ-10 שנים לאחר גמר הבנייה.

תאריך ________ חתימה ________

הצהרת האחראי לביצוע שלד הבניין (כאשר מונה) ☐
אני החתום מטה (שם משפחה ושם פרטי) אליאס הרצל מס זהות 053431235
מהנדס רשוי מס ________/הנדסאי בעל רישיון מס 167781 (ל"מבנה פשוט") מצהיר בזאת כדלקמן:
1) אני מסכים להיות האחראי לבצוע שלד הבניין
2) אני מצהיר, כי יש לי כישורים מקצועיים להיות אחראי לביצוע שלד הבניין, ואני מתחייב לדאוג לביצוע שלד הבניין על פי התכניות והוראות של מתכנן השלד כפי שניתנו בכתב וכן למלא את תפקידי על פי שנקבע בכל חיקוק הנוגע לה.

תאריך 14.3.13 חתימה ________

הצהרת אחראים לביקורת (כאשר מונה) ☐
אנו החתומים מטה מצהירים בזה :
1) כל אחד מאיתנו מאשר שהאמור בנוגע לו ברשימה שבסעיף י"ב לעיל הוא נכון.
2) כל אחד מאיתנו מסכים לקבל עליו את התפקיד המיועד לו בסעיף י"ב.
3) אנו מצהירים כל אחד בנוגע לתחום פעולתו, שיש לנו כישורים מקצועיים לערוך את הביקורת כהלכה ולדווח על תוצאותיה לרשות הרישוי המקומית, כמתחייב על פי כל דין.
אני ________ (עורך הביקורת הראשי) אחראי/ת לכך שהביקורת תיערך על פי מיטב הידיעה המקצועית, ושכל הדיווחים לרשות הרישוי המקומית ייערכו על פי כל דין.

תאריך	שם משפחה ושם פרטי	מספר רישיון	חתימה

על פי טופס 1 תקנה 2(א)

היתר בנייה	מס' הבקשה למידע	מתאריך

ד. חומרי הבנייה

סוג הבנייה: ☐ רגילה ☐ בית סוכן ☐ מתועשת ☐ אחר ________
קירות חיצוניים: ☐ בטון מזוין ☐ בלוקים ☐ אבן מבנית ☐ לבנים שרופות ☐ אחר ________
חומרי גימור: ☐ אבן מלאכותית ☐ אבן מבנית ☐ טיח ☐ זכוכית ☐ אחר ________
תקרות: ☐ בטון מזוין ☐ עץ ☐ אחר ________
גג: ☐ בטון מזוין ☐ רעפים ☐ אסבסט ☐ פח ☐ אחר ________
גדרות: ☐ אבן מבנית ☐ אבן מלאכותית ☐ בטון ☐ בלוקים ☐ ברזל ☐ עץ ☐ רשת ☐ אחר ________
קיימות ____מ"א מוצעות ____מ"א סה"כ ____מ"א

מקרא חומרים (צבעים):

בטון או בטון מזוין	🟦	אישור	☐
בלוקים או לבנים מבטון	🟥	זכוכית	☐
טיקיק או לבנים אדומות	☐	הריסה	🟨
אבן	☐	אחר	☐
עץ	☐		

(ג) סך כל שטחי הבניין

מ"ר	%משטח המגרש	סך כל השטחים המותרים	משטחים לא מקורים פרגולה
74.17	95	74.17	6.89
22.84	29	23.00	
97.01	124	97.17	6.89

הבקשה הראשי
שם אליאס הרצל חתימה ________

14.3.13	שם [illegible]	חתימה
14.3.13	שם [illegible]	חתימה
14.3.13	שם	חתימה
14.3.13	שם אליאס הרצל	חתימה

הערות

תאריך	שם	חתימה

20

005

7 12-1564

עיריית תל-אביב - יפו
מח' רישוי בניה צוות [illegible]
14-03-2013
נ ת ק ב ל

עיריית תל-אביב - יפו
14 [illegible] 2013
נ ת ק ב ל

עיריית תל - אביב - יפו
מינהל ההנדסה , אגף רישוי ופיקוח על הבנייה
שדרות בן-גוריון 68 תל-אביב 64514 (פקס 5231340) טלפון 5217120, 5217045

לכבוד ☐ הועדה המקומית לתכנון ולבנייה
☐ רשות הרישוי המקומית

חוק התכנון והבנייה, התשכ"ה-1965
תקנות התכנון והבנייה (בקשה להיתר תנאיו ואגרות) התש"ל-1970

בקשה להיתר בנייה או לשימוש במקרקעין

יש להקפיד למלא את כל הפרטים בטופס הבקשה ולצרף מסמכים כמפורט ברשימת התיוג המצורפת

מס תיק הבניין: 4062-028
מס' בקשה קודמת ל

א פרטי הנכס והמבקשים

הכתובת	רחוב	מס בית	גוש	חלקה	תת חלקה	מגרש	הוראות התכניות החלות על המקום
	אביטל	28	6135	44			ג, 2215

פרטים אישיים	שם משפחה / שם פרטי או שם חברה או תאגיד	מס' זהות/חברה או מס' רישום תאגיד	רחוב ומספר בית / ישוב ומיקוד	מספר טלפון / מספר פקס
מבקש 1	דוידוב ויטלי	310123278	רח' אביטל 28 ת"א	0502124026
מבקש 2	דוידוב תמרה	306519794	רח' אביטל 28 ת"א	0502124026
מבקש 3				
בעל הזכות בנכס	דוידוב ויטלי דוידוב תמרה	310123278 306519794	רח' אביטל 28 ת"א רח' אביטל 28 ת"א	
החוכר				
עורך הבקשה הראשי	[illegible]	05343235	05343235	0525775755 03-6730730
מתכנן שלד הבניין	[illegible]	05343235	[illegible]	0502124026

ב מהות הבקשה

☐ בקשה לתוספת בנייה ☐ בקשה להרחבת דיור (במסגרת הרחבת דיור שכונתית)

☐ תוספת ______ קומות לבניין

הכוללות: ☐ ______ יחידות דיור

☐ ______

☐ תוספת בנייה בקומה גג ☐ לחזית ☐ לאחור ☐ לצד

בשטח של 22.84 מ"ר

שטח הדירה / המשרד לאחר התוספות יהיה 97.01 מ"ר

☐ שינויים פנימיים הכוללים: ______

☐ אישור מצב קיים

☐ ______

המקום משמש כיום ל- ______

☐ בהיתר ☐ בלי היתר

ג מפרט - תיאור הבקשה

תיאור הקיים על המגרש — פרט מספר מבנים · גובהם · מטעם · ייעודם וכד'.
קיים בנין מגורים בן 2 קומות
שתי יחידות דיור

שימוש עיקרי:
☑ מגורים ☐ מלונאות ☐ תעשיה ☐ חקלאי
☐ משרדים ☐ בידור ☐ בנין ציבורי ☐ מלאכה
☐ מסחר ☐ נופש וספורט ☐ שימוש אחר

סוג העבודה או השימושים המוצעים:
☐ תוספת לבניין ☐ הריסה ☐ שינוי בשימוש
☐ שינוי לבניין ☐ תיקונים
מספרה ______
לספרה ______

הגורם שמבוצעת בעבורו הבנייה:
☐ משרד ממשלתי ☐ מוסד ציבורי ☐ בנה ביתך
☐ רשות מקומית ☑ גורם פרטי ☐ אחר: ______

שטחים	שטח המגרש/החלקה	שטח הבנייה הכולל המבוקש	אחוזי הבנייה
	78 מ"ר	97.01 מ"ר	124 %

אם במסגרת הרחבת דיור שכונתית: מספר יחידות דיור מורחבות ______ מספר תכנית ההרחבה ______

ד. השטחים המבוקשים לבנייה (על-פי תכנית הבנייה) והמותרים לבנייה (על-פי "אסמכתא": חוק, תקנות, תכנית) בכל מפלס בנפרד ולפי שימוש

הקומה/המפלס בבניין (לפי פירוט המופיע בהסברים בכריכת התיק הוורוד - תיק הבקשה להיתר)	(א) שטחי השימוש העיקריים 1) קיים בהיתר	1) קיים ללא היתר ומבוקש לאשר בדיעבד	1) בנייה חדשה מוצעת	1) מותר	2) קיים בהיתר	2) קיים ללא היתר ומבוקש לאשר בדיעבד	2) בנייה חדשה מוצעת	2) מותר	סך כל שטחי הבנייה העיקריים (קיים ומוצע) לשימושים השונים: מ"ר	% משטח המגרש	סך כל השטחים המותרים	ה"אסמכתא" לשטחים המותרים לשימושים העיקריים ולשטחי השרות	(ב) שטחי השירות: מקלט	מתקנים חדרים ומערכות טכניות	החסנה	חניה	מבואות וחדרי מדרגות	קומת עמודים מפולשת	מעברים לכלל הציבור	בליטות	אחר	בנייה קיימת	סך כל שטחי השרות מ"ר: קיים	מ"ר: מוצע	% משטח המגרש	סך כל השטחים המותרים
קומה א'		61.52		61.52					61.52	79	61.52		12.65										12.65		16	12.65
קומת גג			22.84	23					22.84	29	23	ג														
ס"ה מעל הקרקע		61.52	22.84	84.52					84.36	108	84.52		12.65										12.65		16	12.65
ס"ה מתחת לקרקע																										
סה"כ																										

ו. פרטי הבנייה - לשימוש הלשכה המרכזית לסטטיסטיקה

הייעוד	שטח הבנייה ברוטו - לפי ייעוד: פירוט הייעוד (כגון דירות למגורים, בתי מלון וכו')	השטח על פי ההיתר	גודל הדירות לפי מספר חדרים: מספר חדרים	מספר דירות	מספר מגורים
למגורים			1		
להארחה			2		
לעסקים ולמשרדים			3		
לבנייני ציבור			4		
לתעשייה ולמלאכה			5		
למשק חקלאי			6		
למקלט או למתקן					
למבני עזר					
סך כל שטח הבנייה			סה"כ		

מספר היתר הבנייה ______

	שנה	חודש
תאריך היתר הבנייה		
תאריך התחלת הבנייה		
תאריך גמר הבנייה		

מספר הקומות כולל קומת עמודים מפולשת ______

ז. קווי בנייה

הכיוון		קווי בניה (מטר): מוצע	מותר	הסטייה: במספר	ב-%
כרחוב (שם)	אביטל	0.0	0.0		
כרחוב (שם)	מושיע	0.0	0.0		
לצד	קיר משותף	0.0	0.0		
לאחור	קיר משותף	0.0	0.0		

ח. מספר יחידות דיור

אם השימוש המבוקש הוא מגורים - רשום להלן:
מספר הדירות קיימות: מגד ל - סף לד ______ מספר הדירות המבוקשות ______ מספר הדירות המותרות ______

ט. הבקשה מוגשת לאישור

☐ הוועדה המקומית
הבקשה כוללת בקשה להקלה - כלהלן:

פירוט הבקשה להקלה	נימוקי הבקשה להקלה
1.	
2.	
3.	

☐ רשות הרישוי המקומית
☐ רשות הרישוי המקומית באמצעות מורשה להיתר

לשימוש המשרד	התוכנית תואמת את המצב בשטח		מס' הדוח/התביעה	הנדון בדוח / הנדון בתביעה
הערות הפיקוח	☐ כן ☐ לא	☐ הוכן דוח לתביעה משפטית ☐ הוגשה תביעה משפטית ☐ הוגשה תביעה חוזרת	תאריך הדוח/התביעה	

י. הצהרת עורך

☐ אני מצהיר על נכ

תאריך [illegible].3.13

יא חתימות נוספות

המבקש	תארי
בעל הזכות בנכס/ בעל הנכס/ החוכר	תארי תארי
מתכנן שלד הבניין	תארי