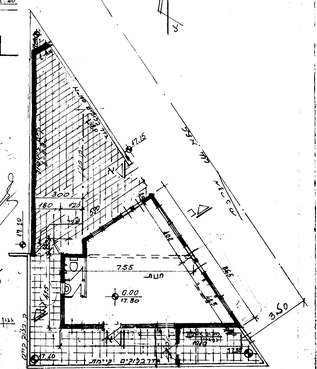
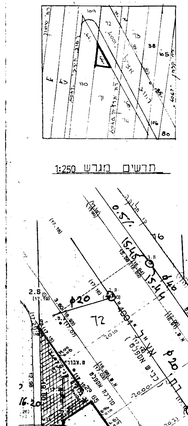
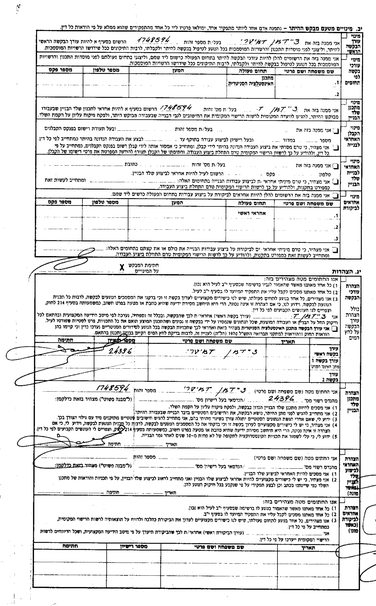
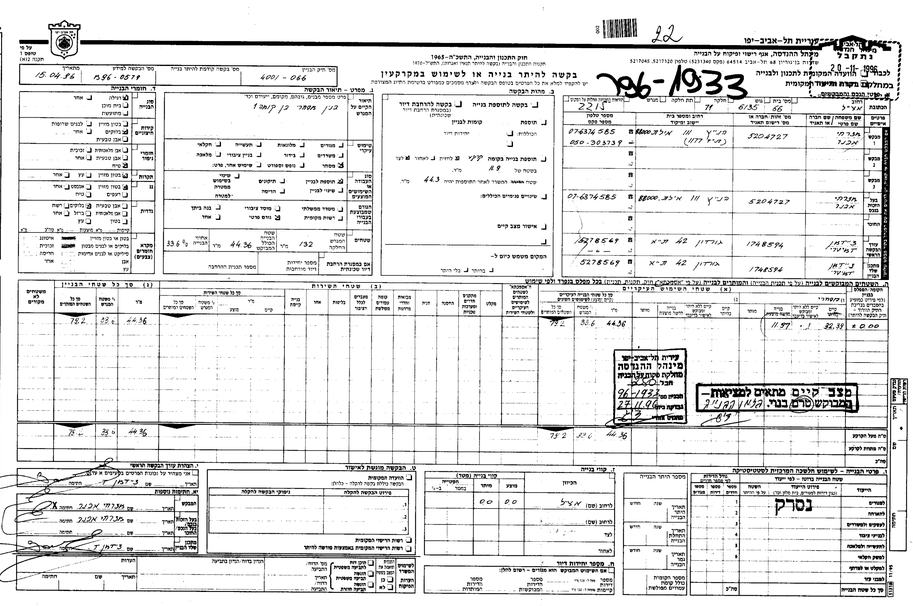

חתך ב-ב
חתך א-א
חזית מזרחית
חזית צפונית
חתך ג-ג
חתך ד-ד
חתך מערבית
חתך מזרחית


תכנית קומת קרקע
חשוב עשות
שטח נויים 32.38=(4.15+4.45):2×7.55
שטח נוצוץ 11.97=4.82×5.30:2-12.48:2
סה"כ שטח בניה 44.36 מ"ר


תרשים סביבה 1:1250
תרשים נגיש 1:250




עיריית תל-אביב-יפו
בקשה להיתר בנייה או לשימוש במקרקעין
נגרק
מבצע יום מתאים למשיאות
מבוקש שרים בנר.
מספר בקשה 1933-96
מספר תיק בניין 0756
מספר בקשה 1933-96